Análisis Georreferenciado sociodemográfico y económico de **TLAXCALA**

NOVIEMBRE **2025**

INEGI

inegi.org.mx

INTRODUCCIÓN

Tlaxcala es uno de los estados más pequeños del país, pero también uno de los que más sorpresas guarda cuando miramos sus datos con detalle. A simple vista, pareciera que todo está cerca, que los municipios se parecen entre sí y que la población sigue un ritmo estable… pero los números cuentan otra historia.

Cuando analizamos cómo se distribuyen las personas, qué municipios están creciendo de manera acelerada, cuáles se están vaciando, dónde se concentra la riqueza, dónde falta empleo formal y en qué regiones persisten altos niveles de pobreza, descubrimos un Tlaxcala muy distinto al que imaginamos.

POBLACIÓN TOTAL EN TLAXCALA, 1995-2020

Entre 1995 y 2020, Tlaxcala pasó de 883 924 habitantes a 1 342 977, un aumento aproximadamente de 51.9%.

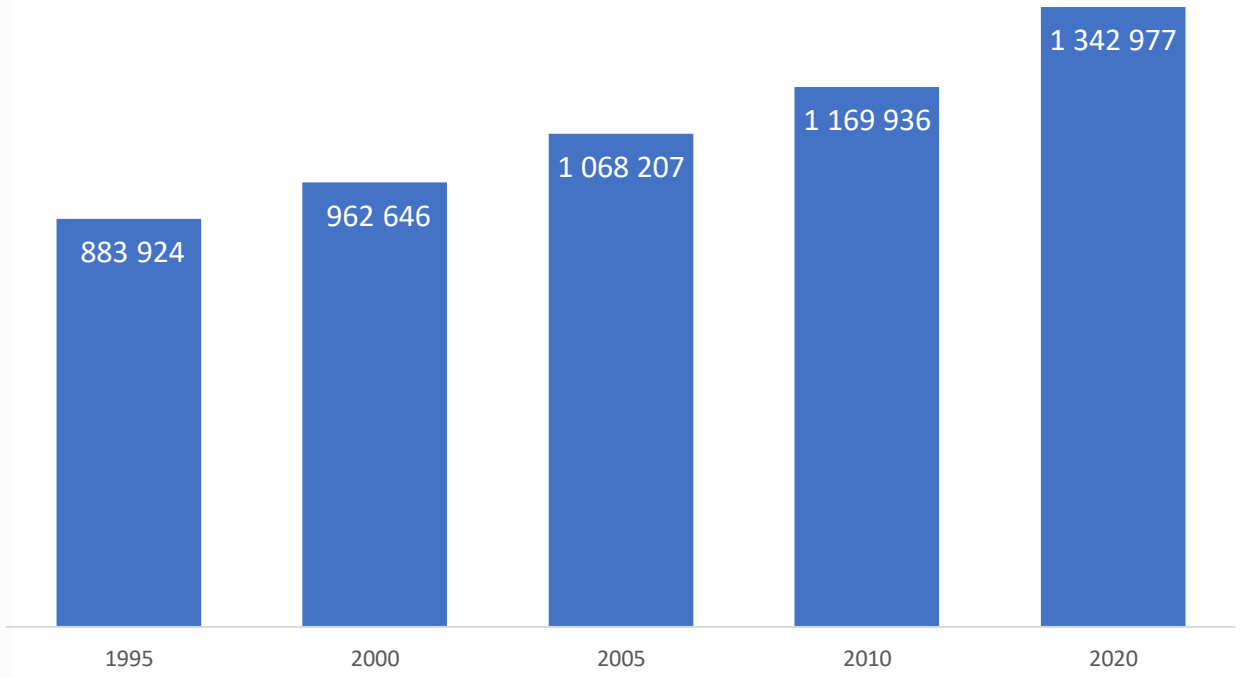

inegi.org.mx

GRAFICO DE DISPERSIÓN DE TASA DE CRECIMIENTO POR PERIODO,**2000-2020**

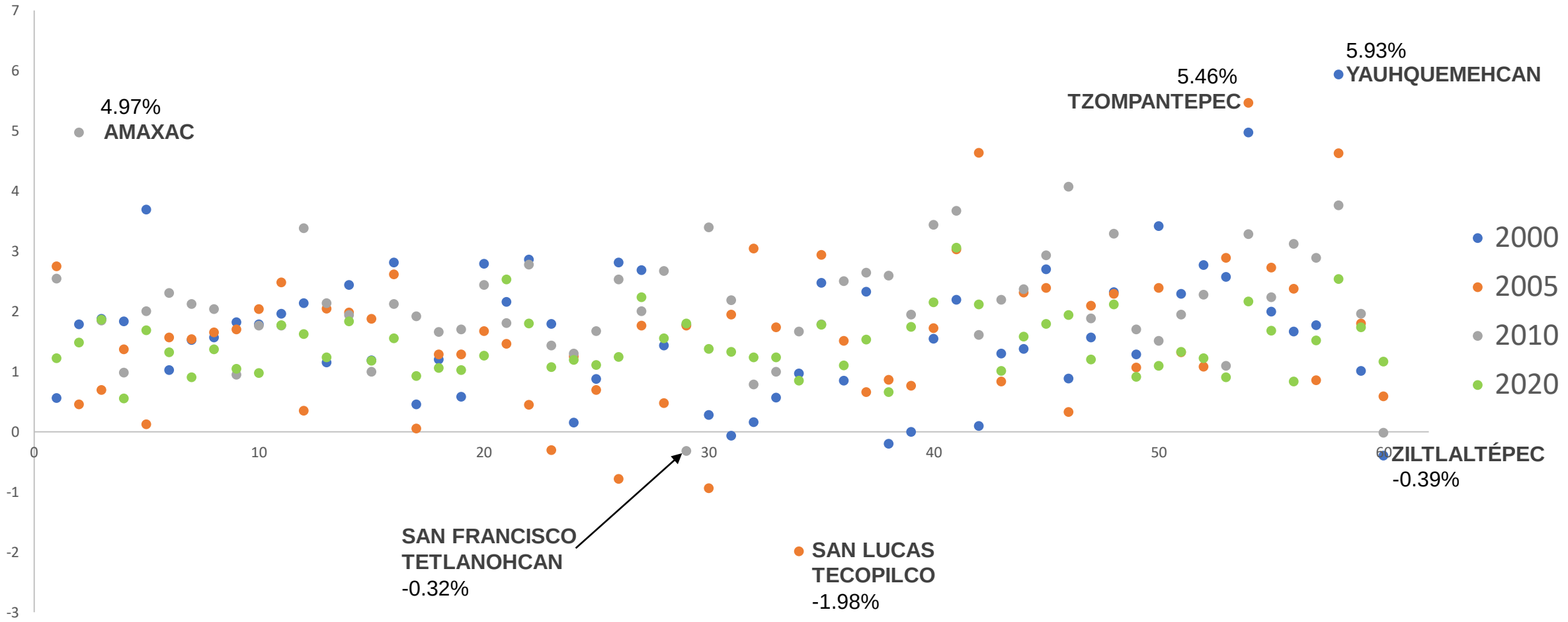

Fuente: INEGI. Censo de población y vivienda, 2000-2020.

inegi.org.mx

DISTRIBUCIÓN DE LA **POBLACIÓN, 2020**

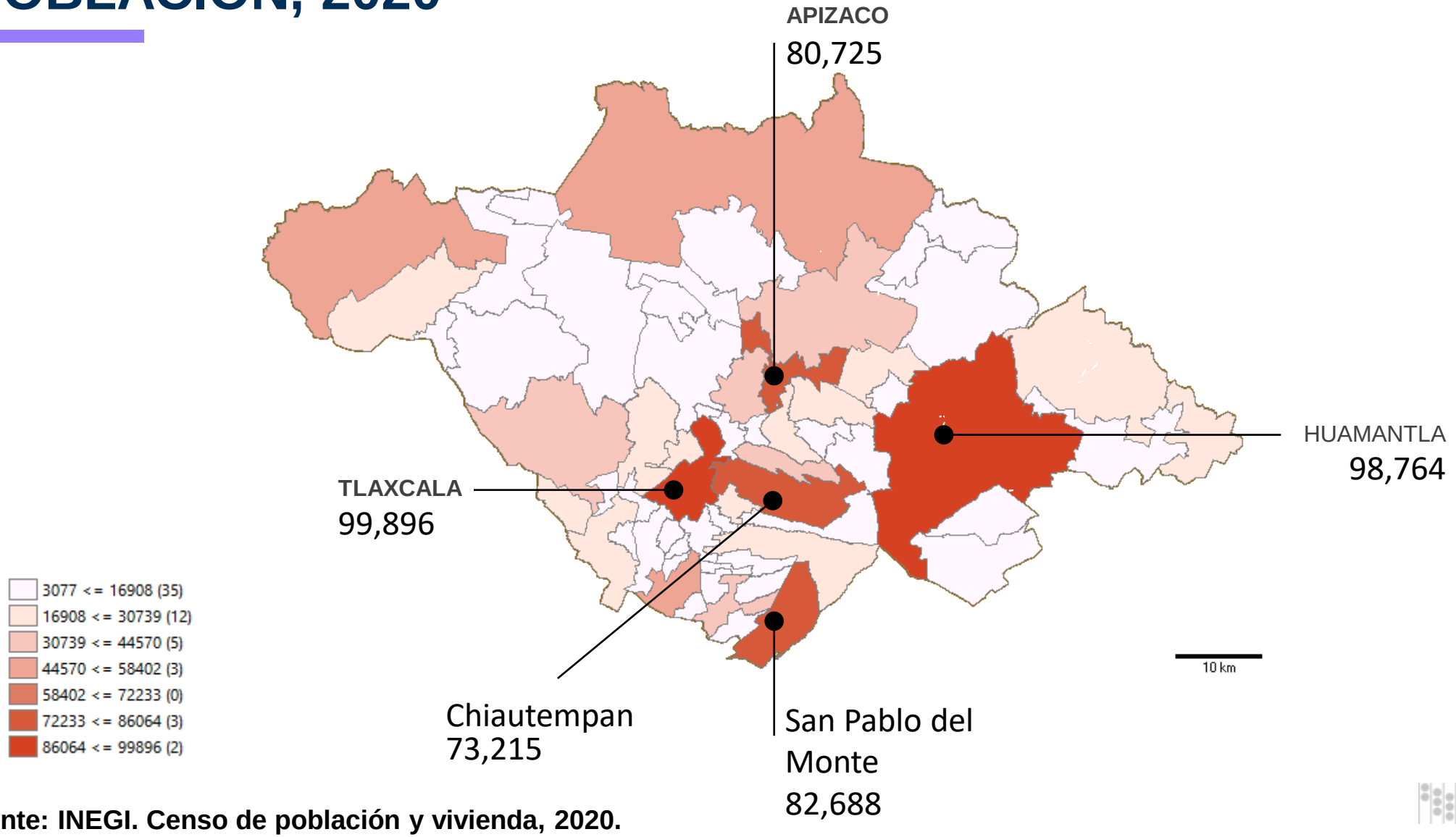

Fuente: INEGI. Censo de población y vivienda, 2020.

inegi.org.mx

TASA DE CRECIMIENTO POBLACIONAL **ANUAL POR MUNICIPIO, 2020**

El municipio con mayor tasa de crecimiento es Santa Cruz Tlaxcala con un 3.1%, y el municipio con menos crecimiento es Apizaco con 0.6%

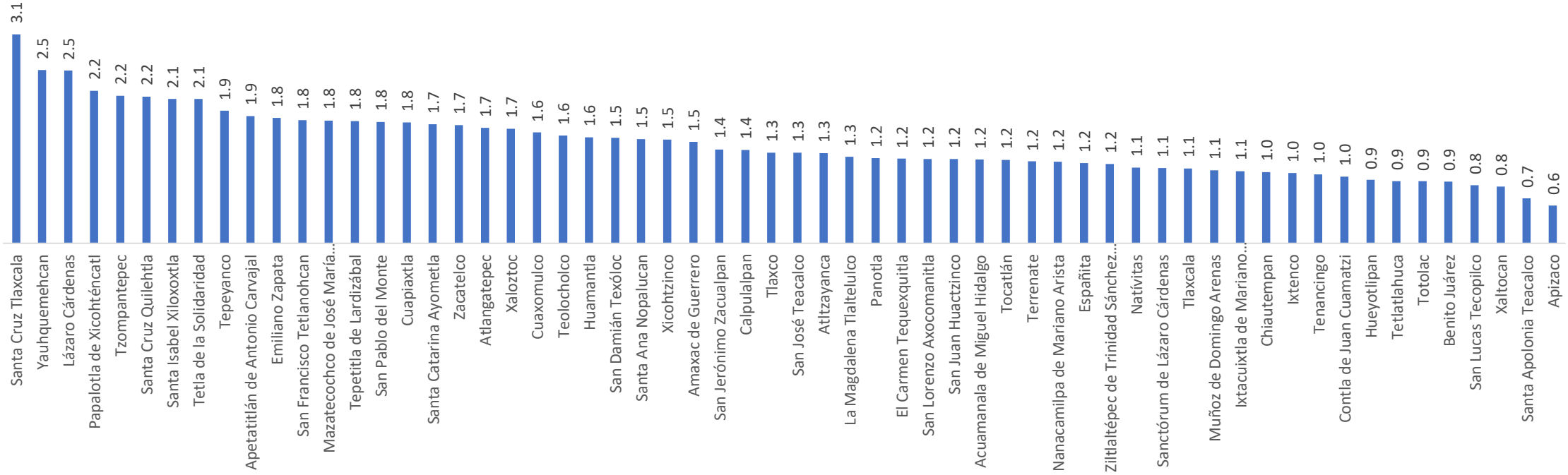

Fuente: INEGI. Censo de población y vivienda, 2020.

inegi.org.mx

DENSIDAD **POBLACIONAL**

Sirve para la **planificación urbana y la gestión de recursos**, ya que informa sobre cómo distribuir personas, servicios e infraestructura en un área determinada. También tiene implicaciones en la **calidad de vida** al influir en la saturación de servicios públicos, los precios de la tierra y la presión sobre los recursos naturales.

Fuente: https://cuentame.inegi.org.mx/explora/poblacion/densidad/, **19/11/2025.**

inegi.org.mx

DENSIDAD DE **POBLACIÓN POR ESTADO, 2020 (HABITANTES POR** KM^2**)**

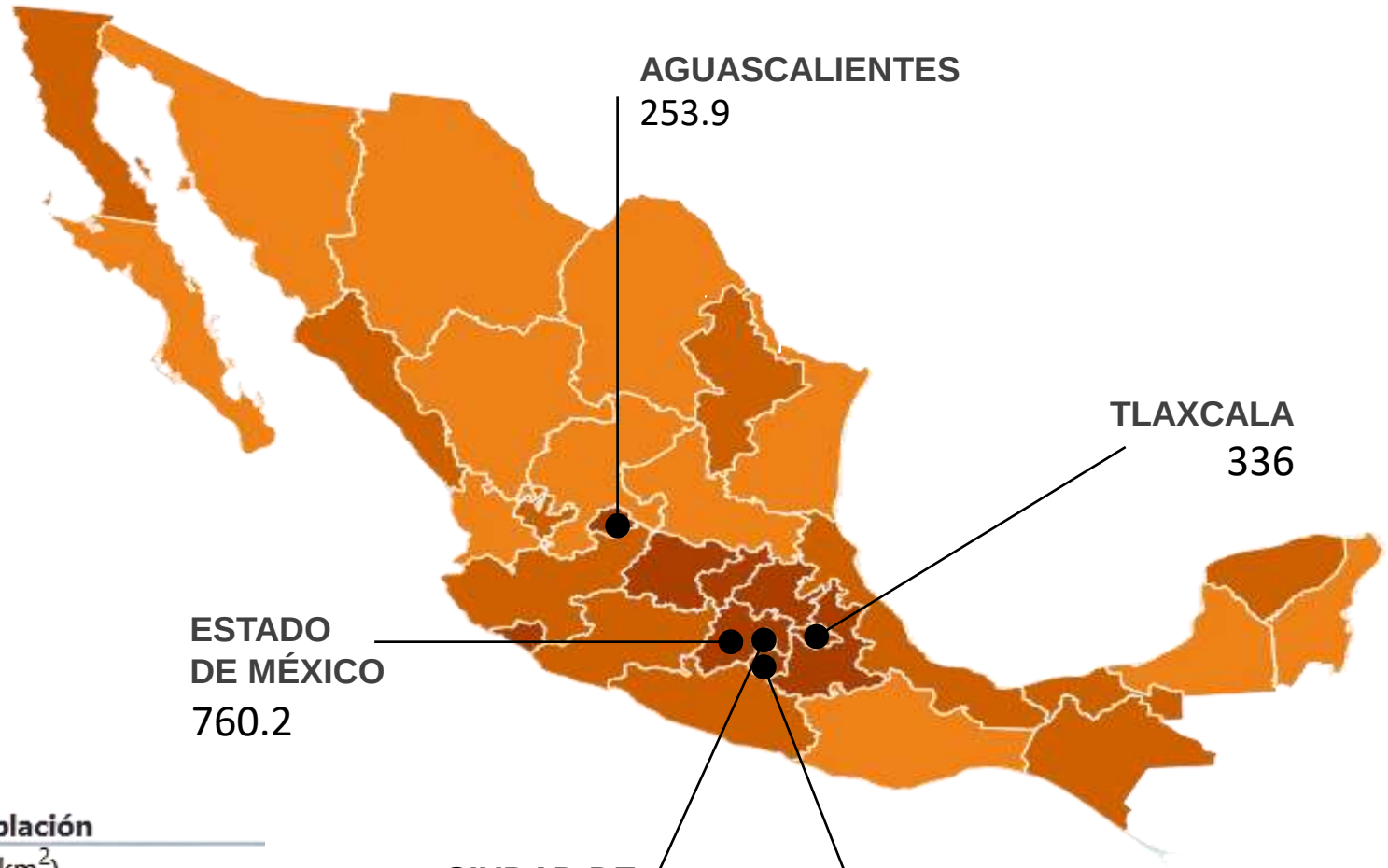

Nivel de densidad de población

- Alto (mayor de 120 hab./km^2)
- Medio (mayor de 46 y hasta 120 hab./km^2)
- Bajo (hasta 46 hab./km^2)

Fuente: INEGI. Censo de población y vivienda, 2020.

inegi.org.mx

EVOLUCIÓN DE LA DENSIDAD POBLACIONAL POR KM^2 EN **TLAXCALA**

221
hab/km^2

1995

240
hab/km^2

2000

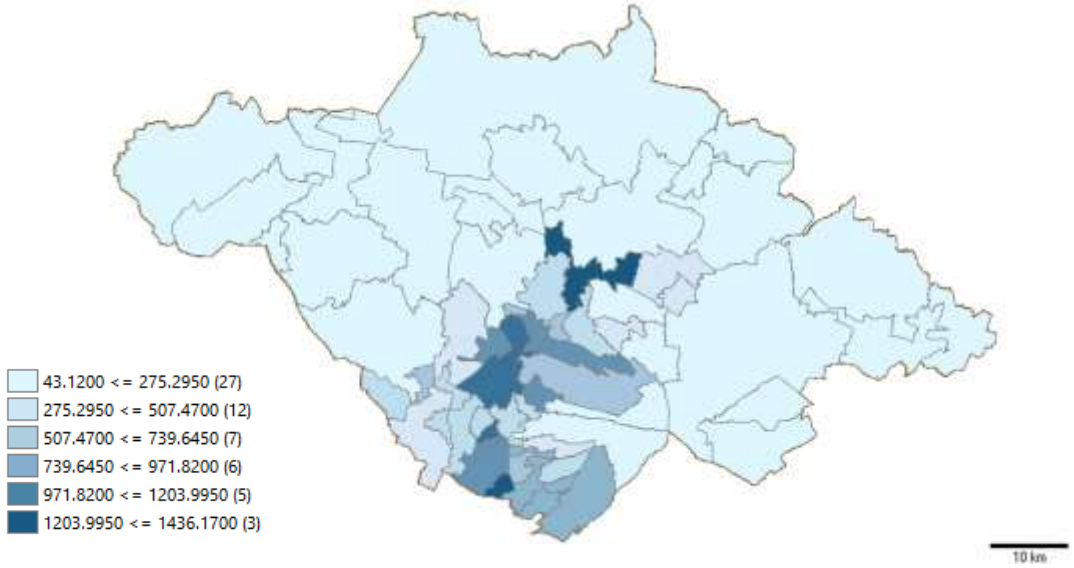

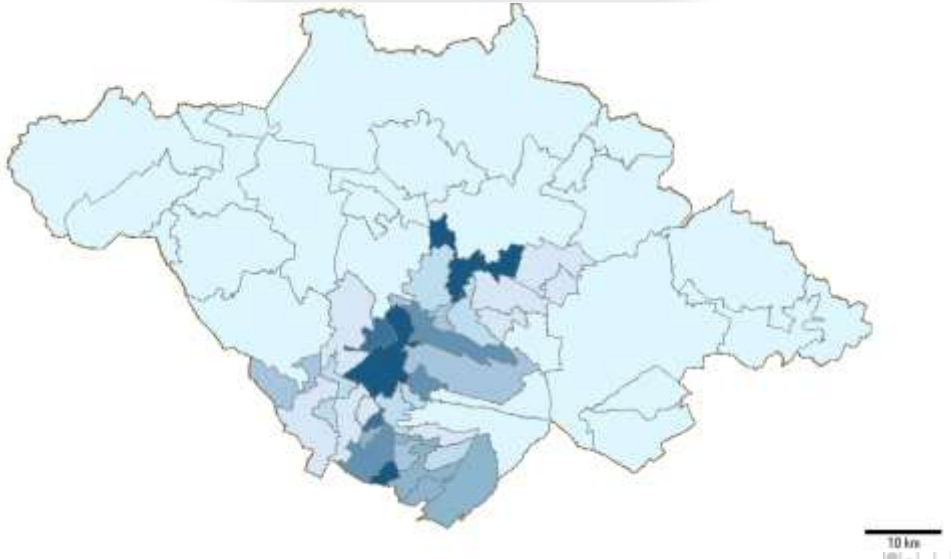

inegi.org.mx
INEGI

EVOLUCIÓN DE LA DENSIDAD POBLACIONAL POR KM^2 EN **TLAXCALA**

267
hab/km^2

2005

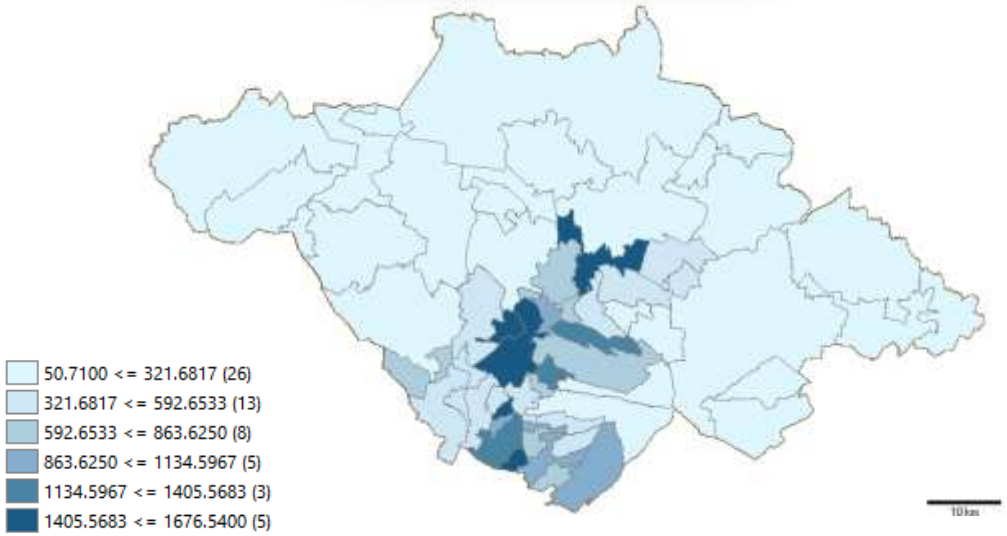

292
hab/km^2

2010

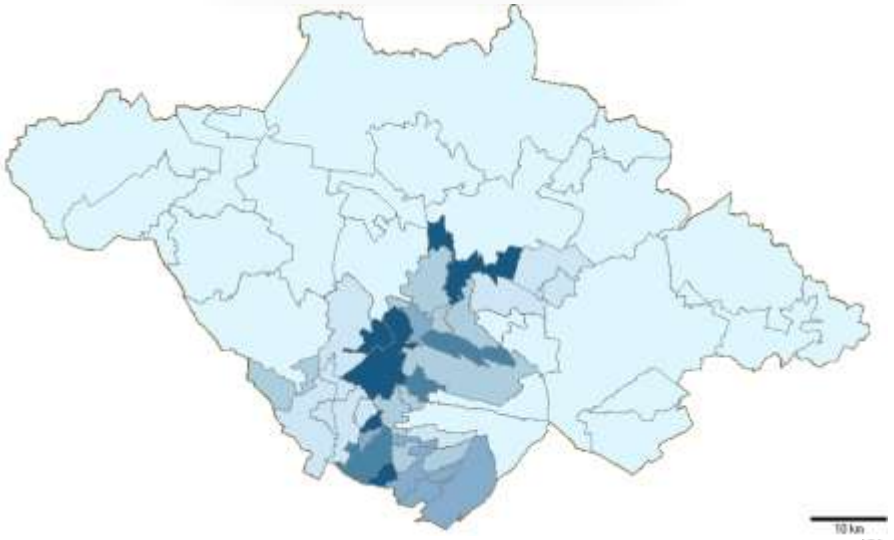

inegi.org.mx
INEGI

PRINCIPALES MUNICIPIOS CON MAYOR DENSIDAD POBLACIONAL POR KM^2 , **2020**

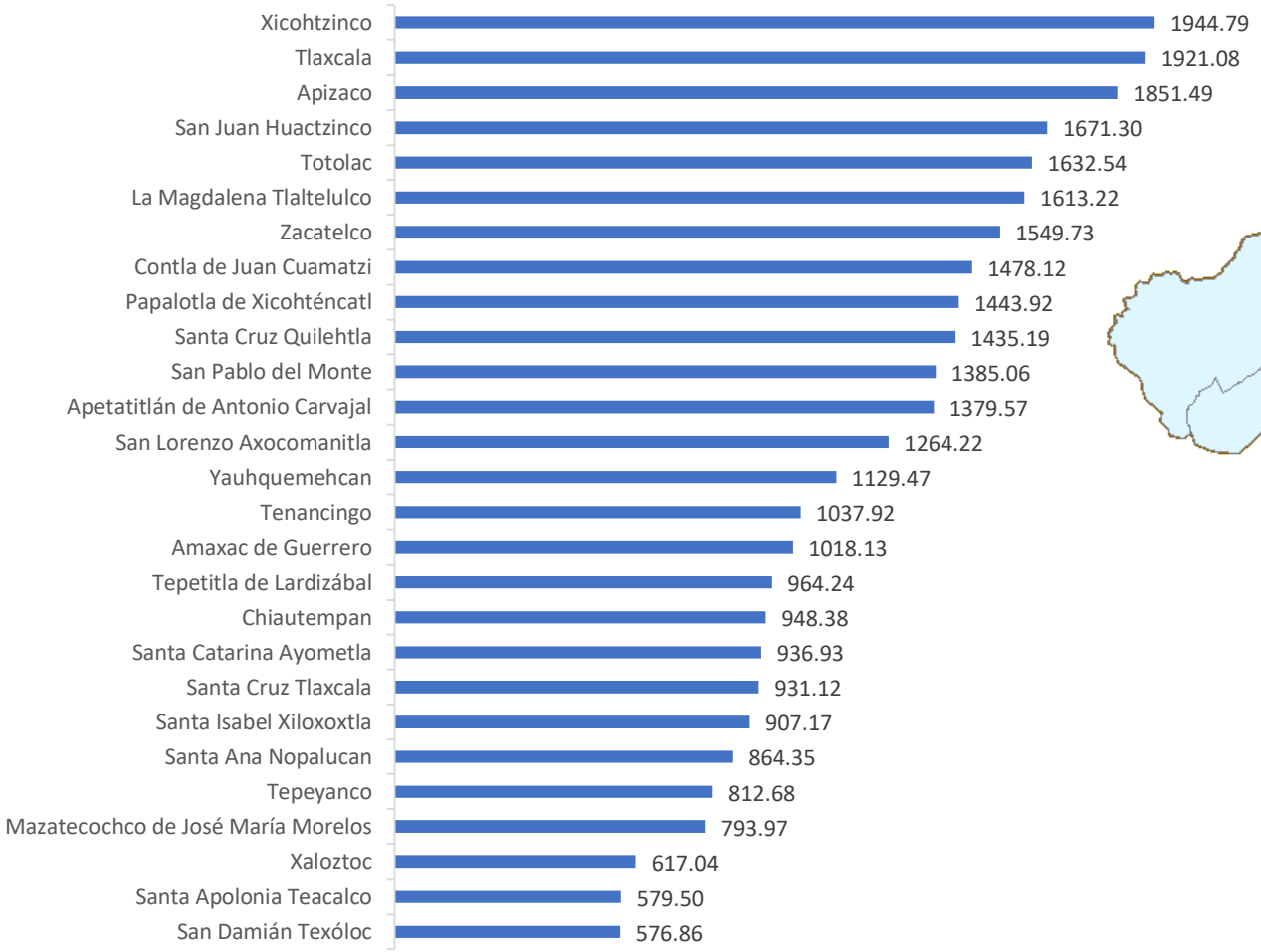

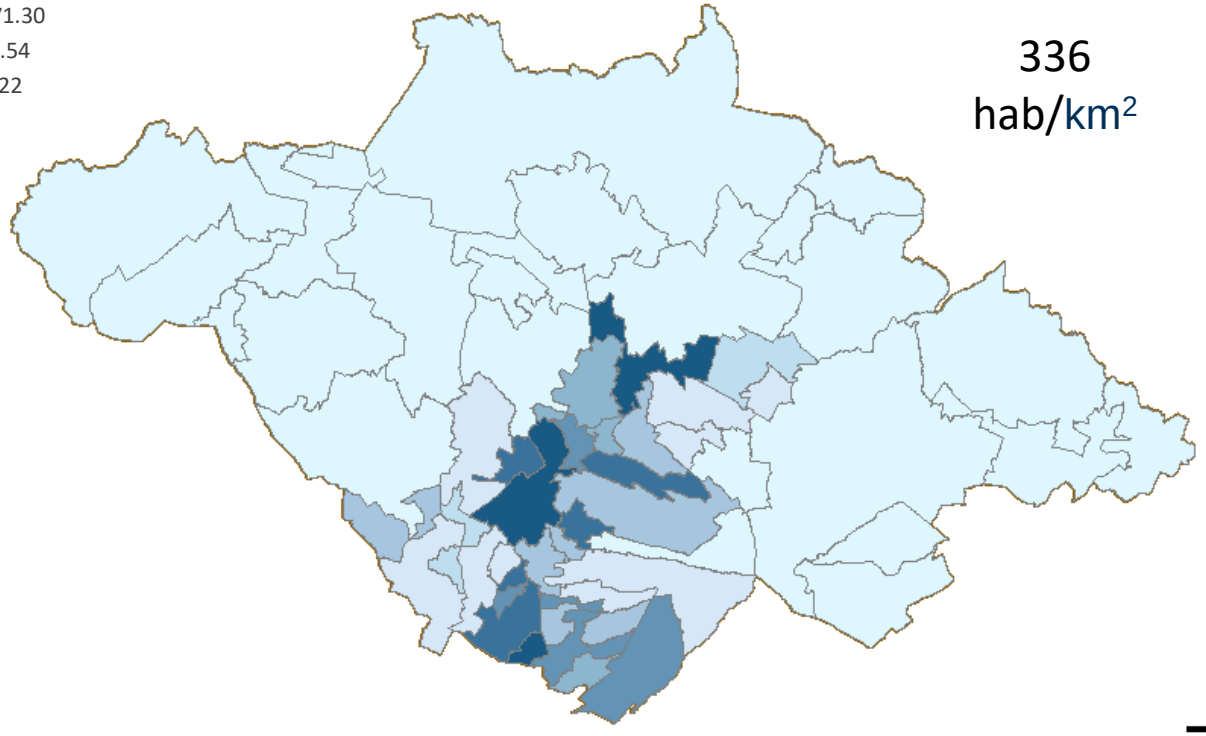

336 hab/km^2

Fuente: INEGI. Censo de población y vivienda, 2020.

inegi.org.mx

PRINCIPALES MUNICIPIOS CON MAYOR DENSIDAD POBLACIONAL SEGÚN PROYECCIÓN **2030**

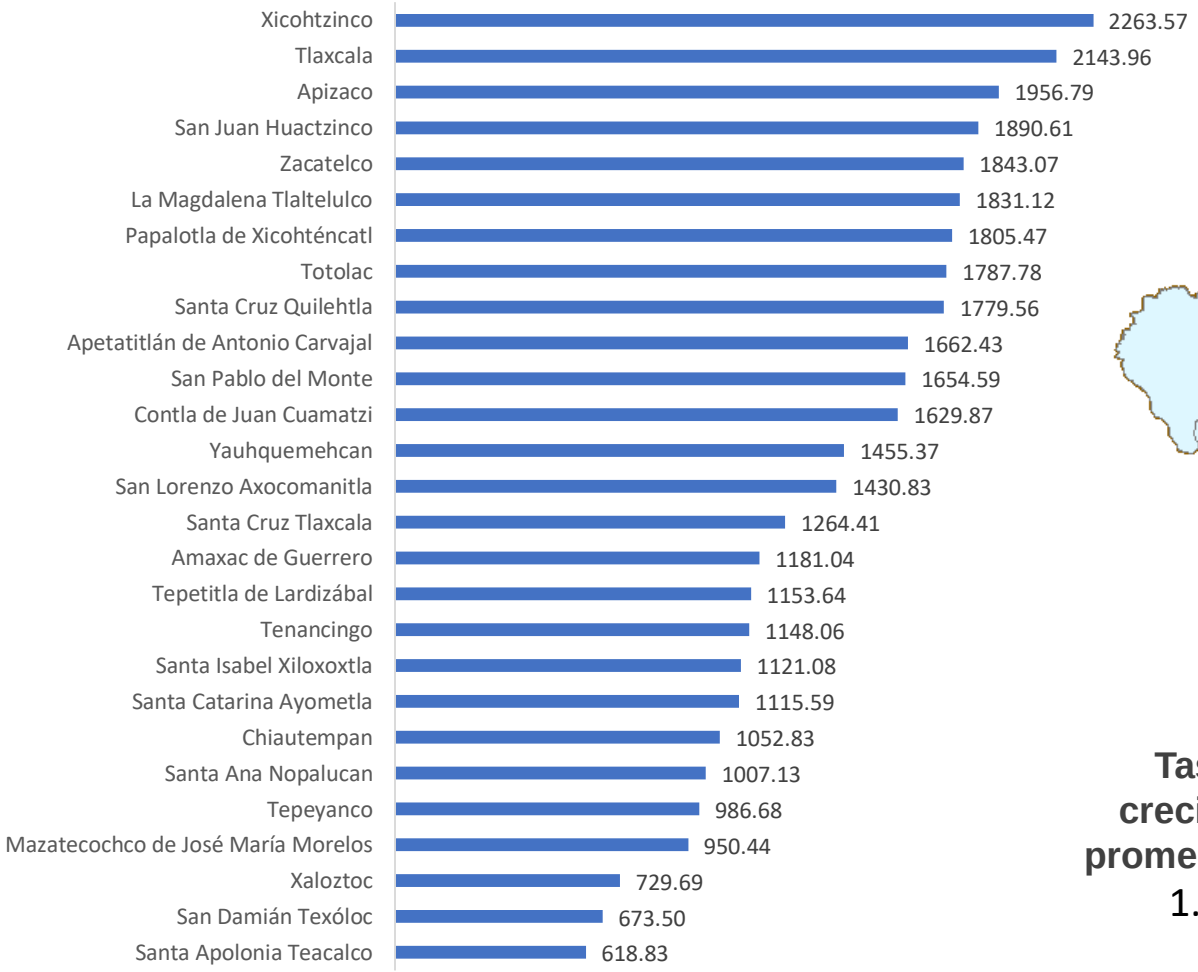

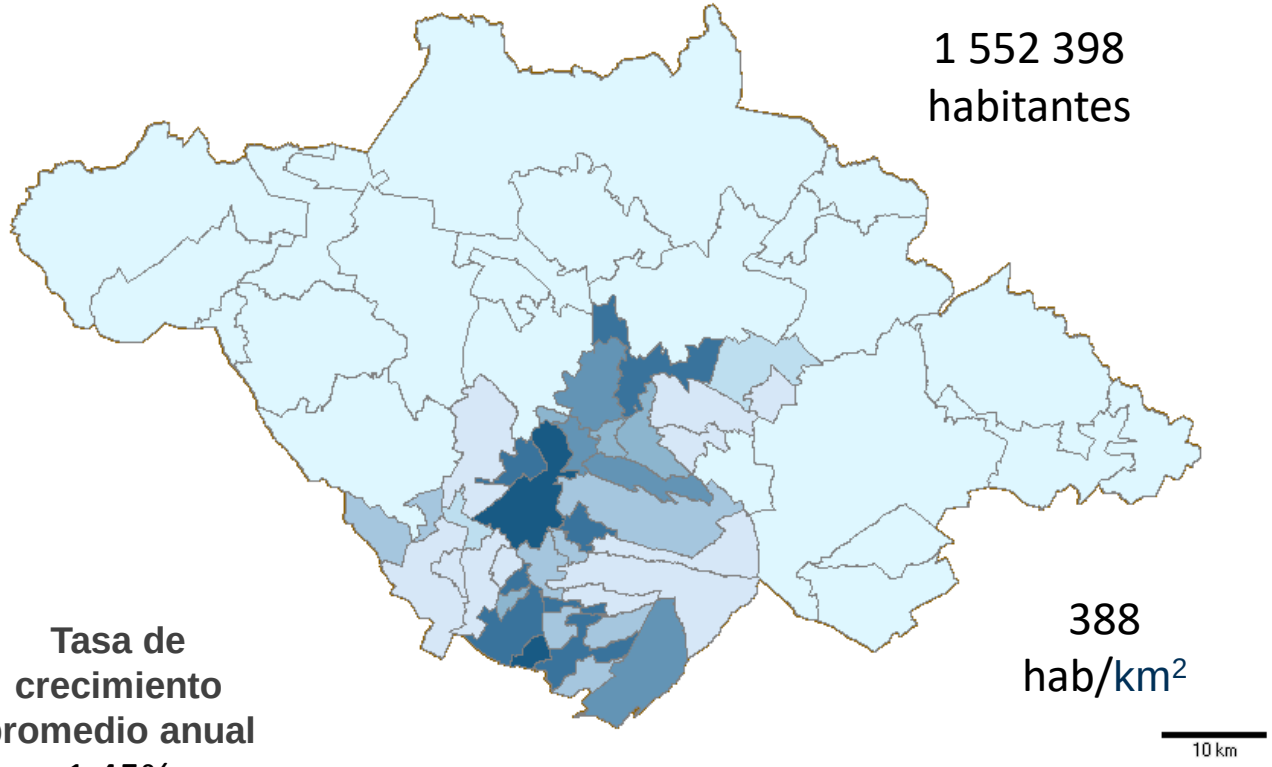

1 552 398 habitantes

388 hab/km^2

Tasa de crecimiento promedio anual
1.45%

inegi.org.mx

INEGI

DISTRIBUCIÓN DE POBLACIÓN POR **TIPO DE LOCALIDAD**

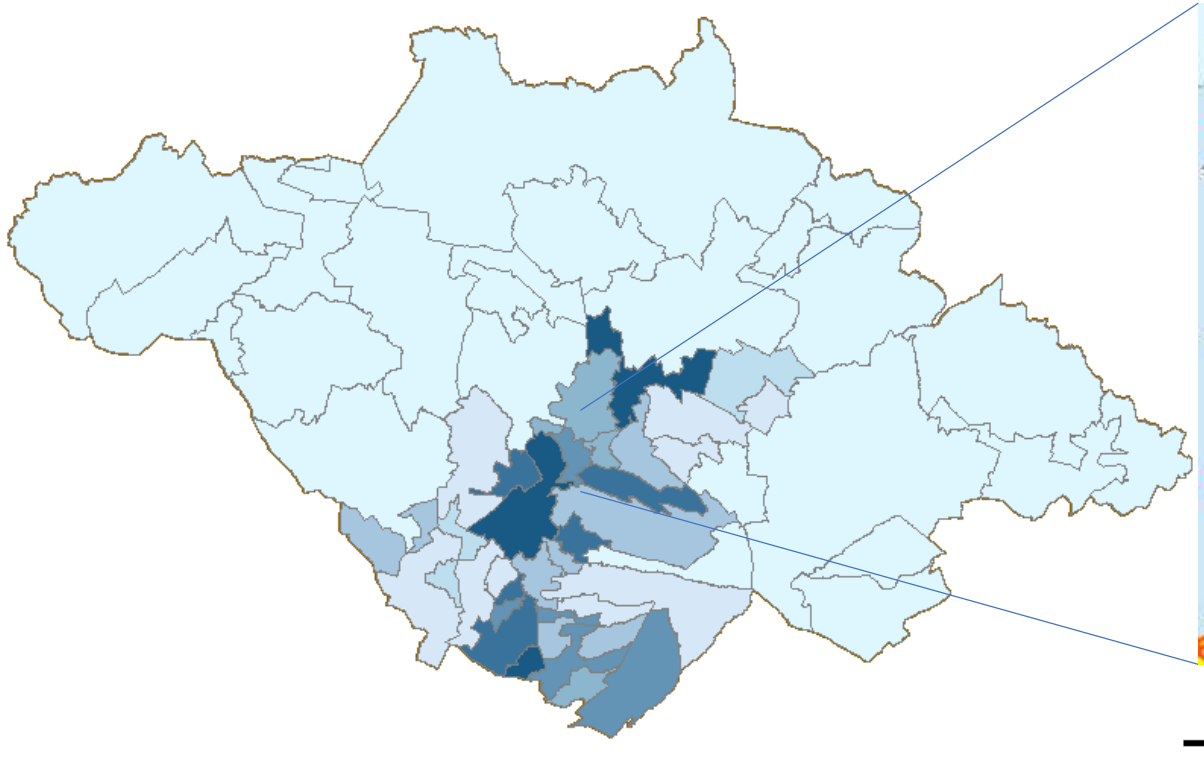

Zonas con más localidades urbanas

INEGI

DISTRIBUCIÓN DE POBLACIÓN POR **TIPO DE LOCALIDAD**

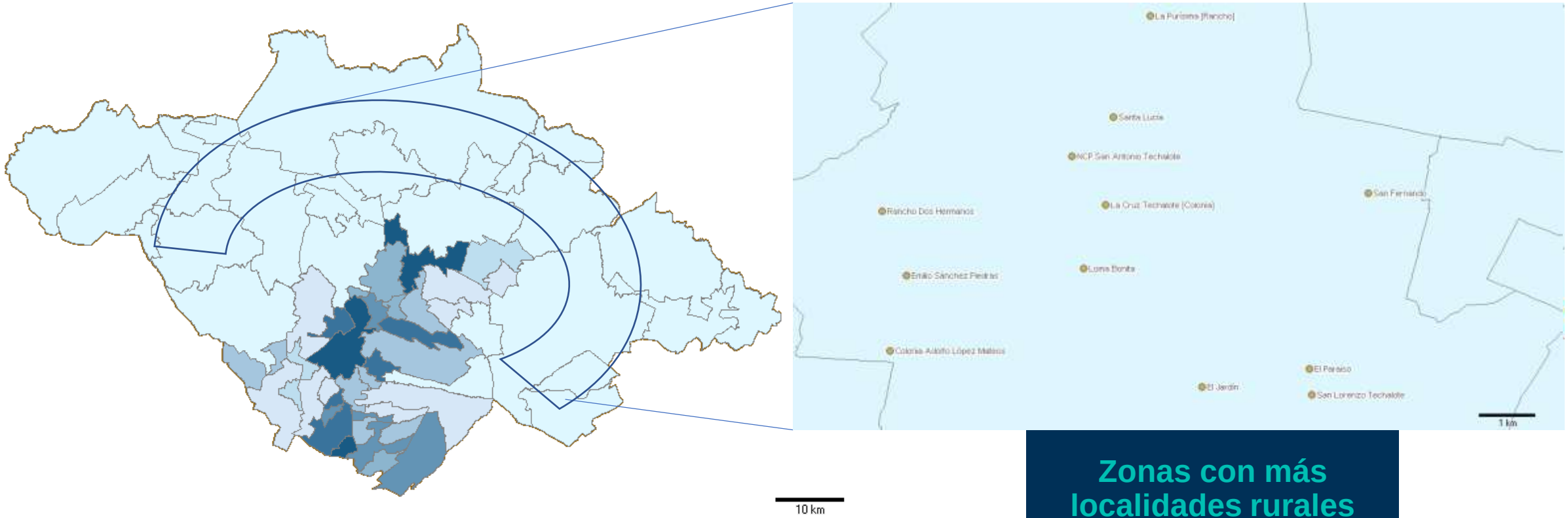

Zonas con más localidades rurales

INEGI

PIB
PER CAPITA

Para medir y conocer todo lo que se produce en un país, las y los economistas utilizan un concepto que se llama Producto Interno Bruto o PIB. Este es la suma de valor, en dinero, de todos los bienes y servicios que se generan durante un periodo (generalmente un año o cada tres meses). Cuando dividimos ese monto de dinero entre la cantidad de personas que viven en un país, se obtiene lo que llamamos PIB per cápita.

- **¿Sabías que, si repartiéramos entre toda la población el dinero que México generó en 2024, a cada persona le corresponderían 192,311 pesos?**

Fuente: https://cuentame.inegi.org.mx/explora/economia/pib_per_capita/, **19/11/2025.**

inegi.org.mx

PIB PER CAPITA **POR ESTADO 2023**

Fuente: INEGI. Sistema de Cuentas Nacionales de México.

inegi.org.mx

VALOR AGREGADO CENSAL BRUTO PER CAPITA POR **MUNICIPIO, 2024**

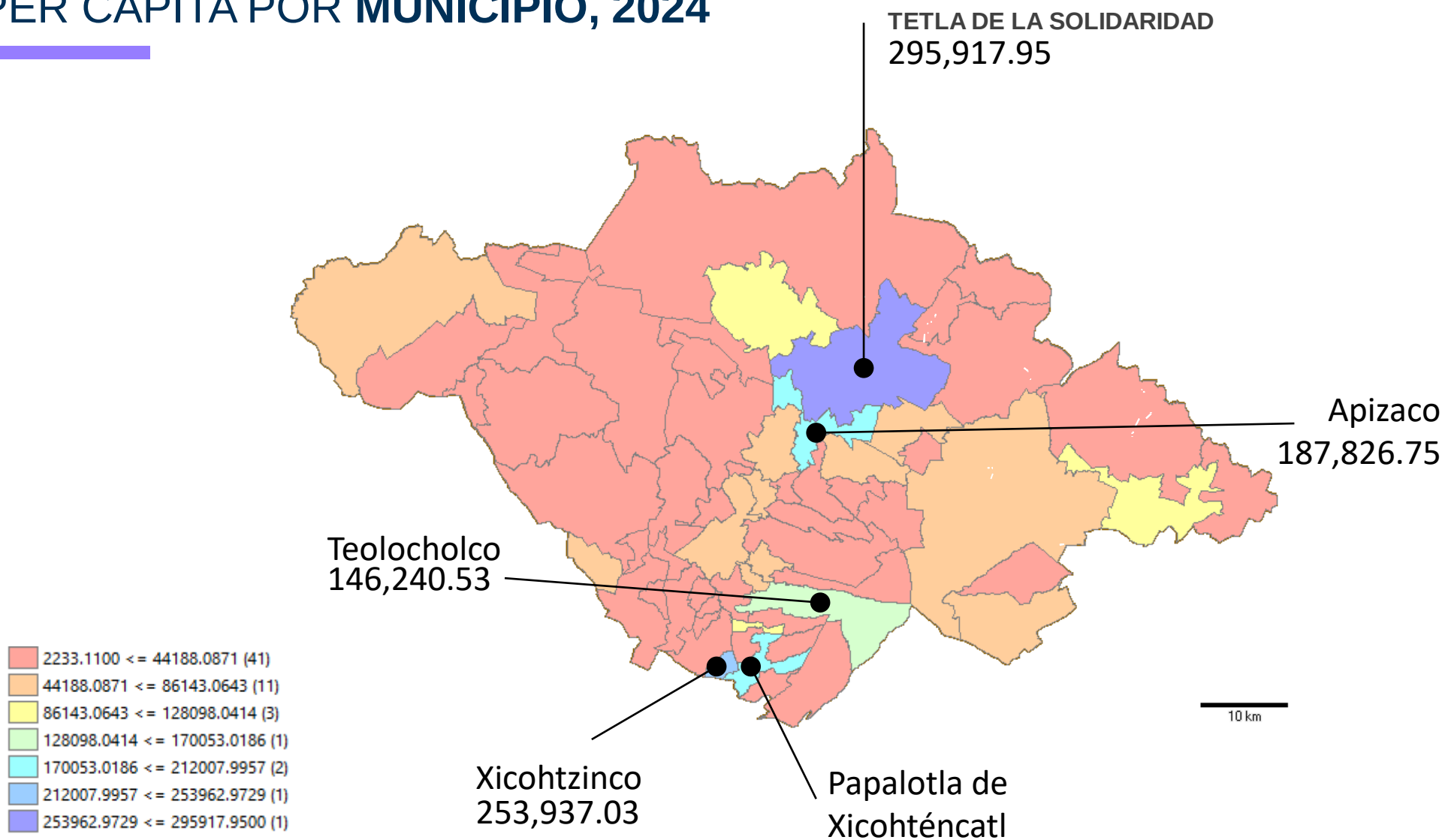

Fuente: INEGI. Censo Económico, 2024.

inegi.org.mx

DISTRIBUCIÓN DE LA POBLACIÓN EN EDAD DE **TRABAJAR**

segundo trimestre de 2025

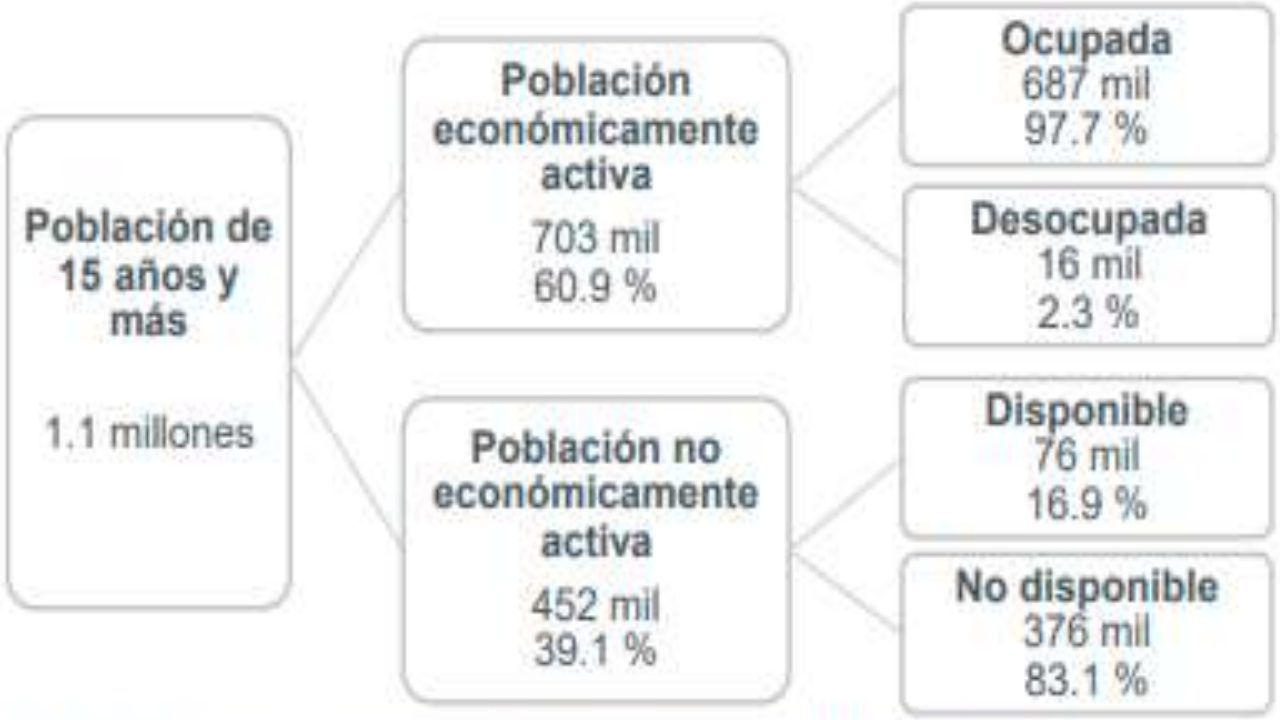

Fuente: INEGI. Encuesta Nacional de Ocupación y Empleo (ENOE), 2025.

inegi.org.mx

INEGI

TASA DE INFORMALIDAD LABORAL
POR ESTADO, 2T-2025

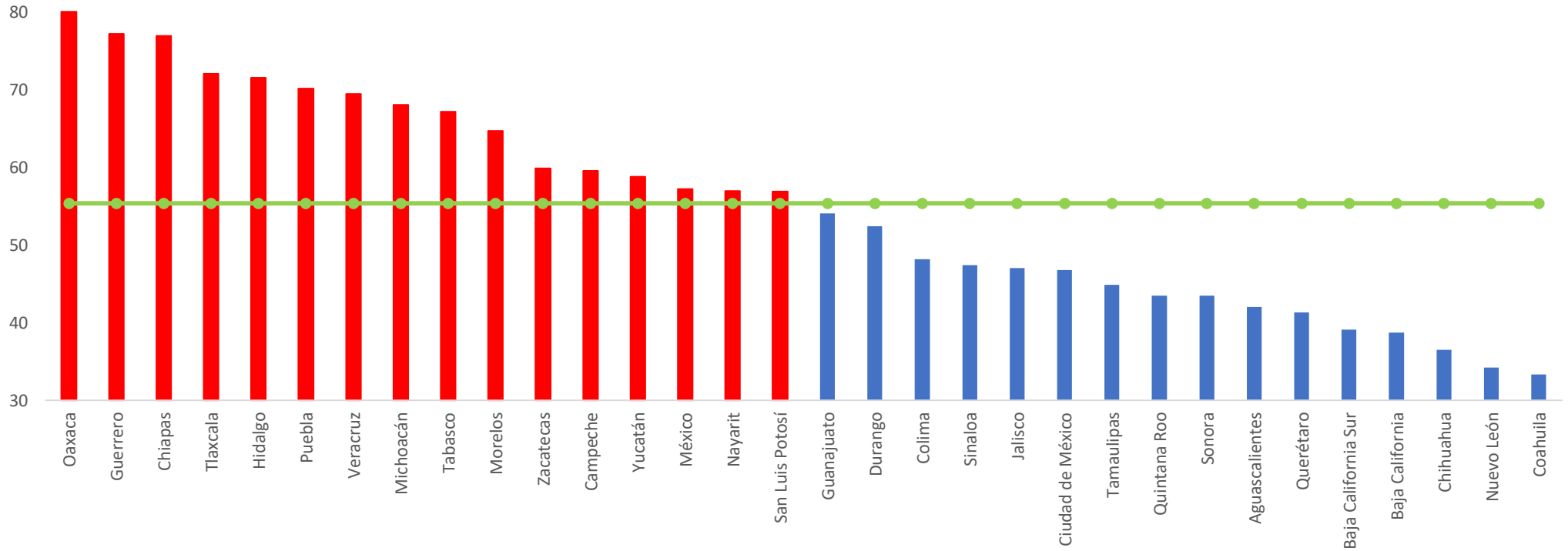

Tlaxcala tiene la 4ª tasa más alta de informalidad a nivel nacional, ya que el 72.2% de los trabajadores del estado tienen un empleo sin prestaciones laborales o vínculo reconocido.

Fuente: INEGI. Indicadores laborales para municipios, 2T-2025.

inegi.org.mx

TASA DE INFORMALIDAD LABORAL **POR ESTADO, 2T-2025**

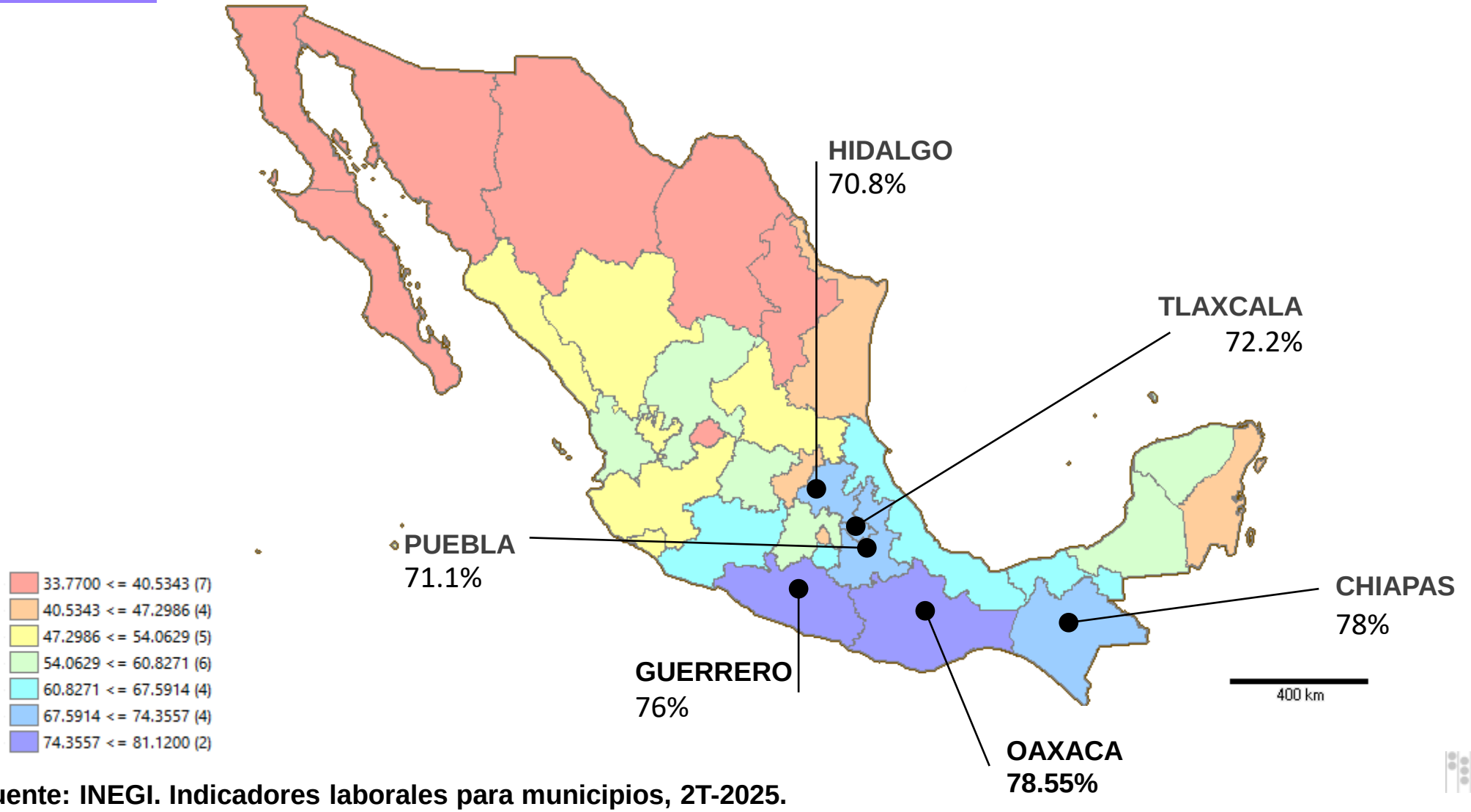

Fuente: INEGI. Indicadores laborales para municipios, 2T-2025.

inegi.org.mx

TASA DE INFORMALIDAD LABORAL
POR MUNICIPIO, 2T-2024

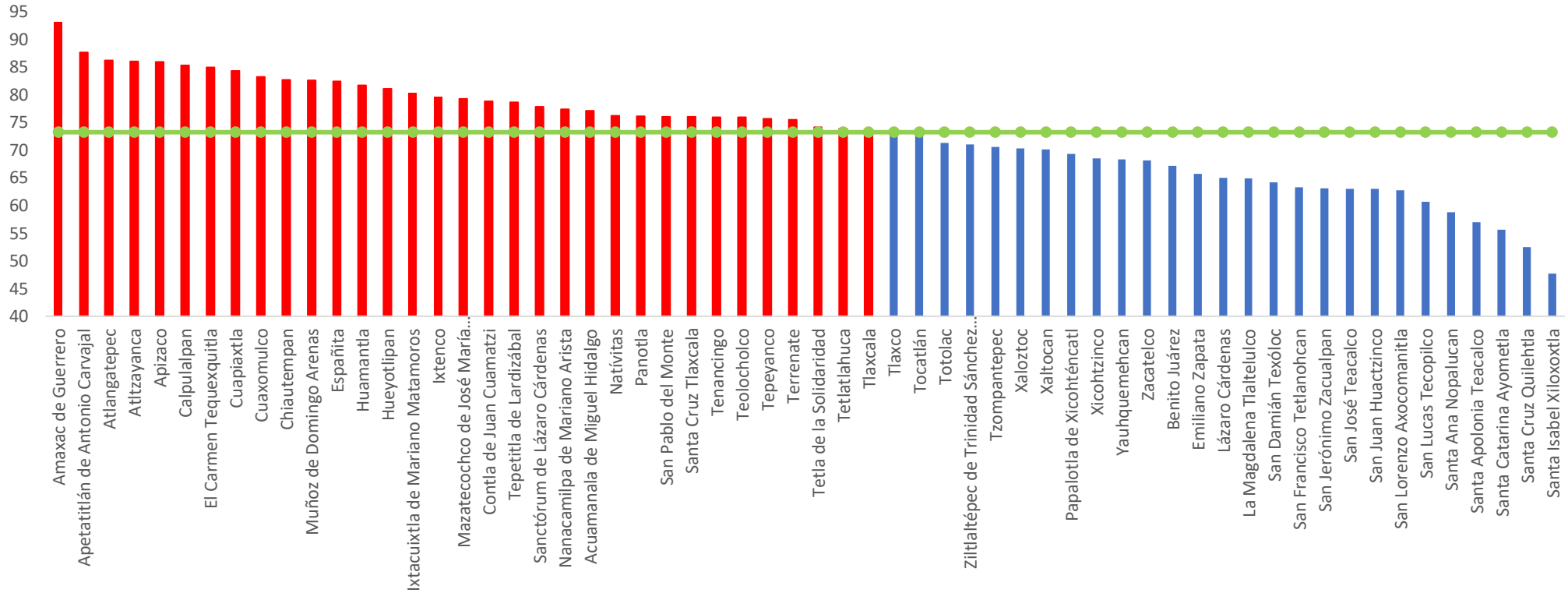

Santorum tiene la tasa más alta de informalidad de Tlaxcala con un 93%, mientras que Acuamanala tiene la menor tasa con 47.68%.

Fuente: INEGI. Indicadores laborales para municipios, 2T-2024.

inegi.org.mx

TASA DE INFORMALIDAD POR **MUNICIPIO, 2T-2024**

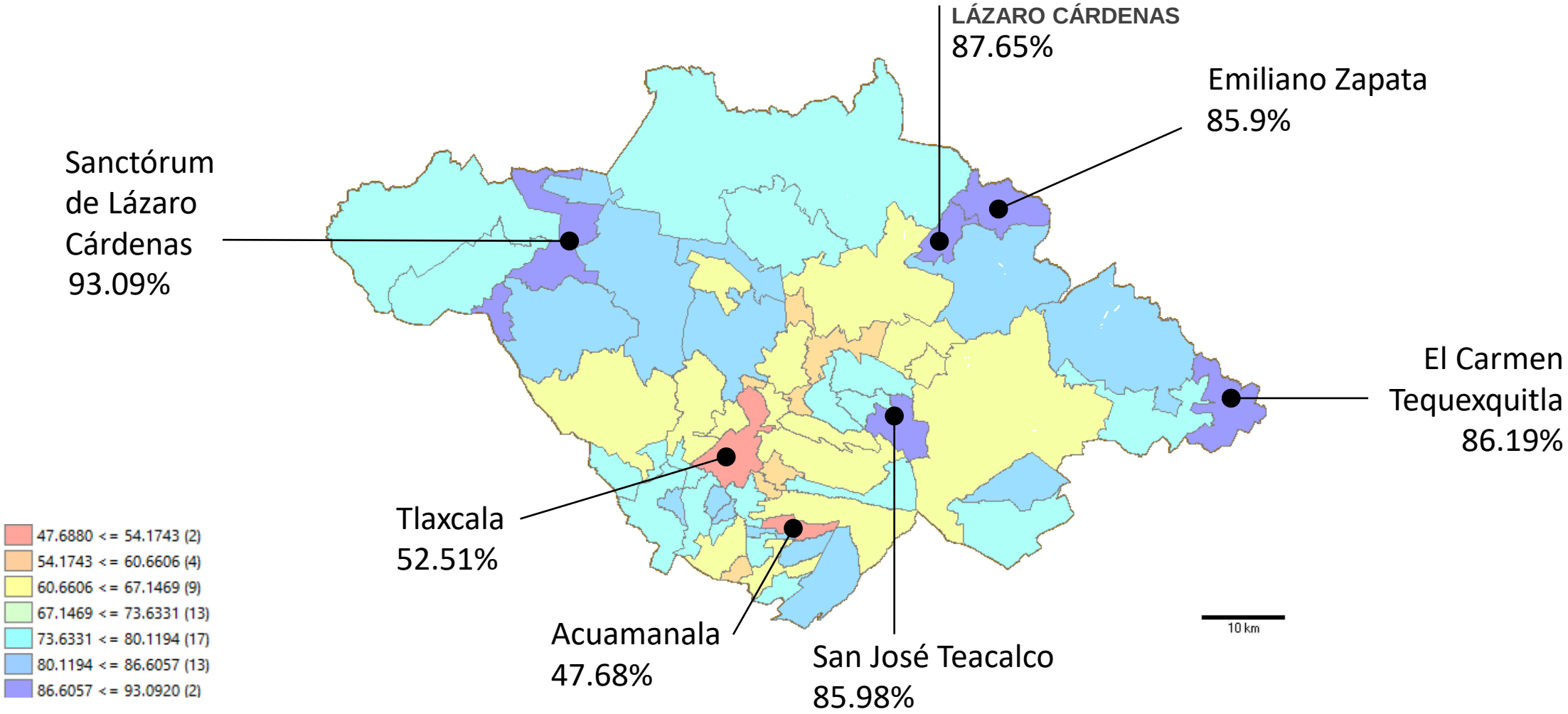

Fuente: INEGI. Indicadores laborales para municipios, 2T-2024.

inegi.org.mx

PROPORCIÓN DE POBREZA POR **MUNICIPIO, 2020**

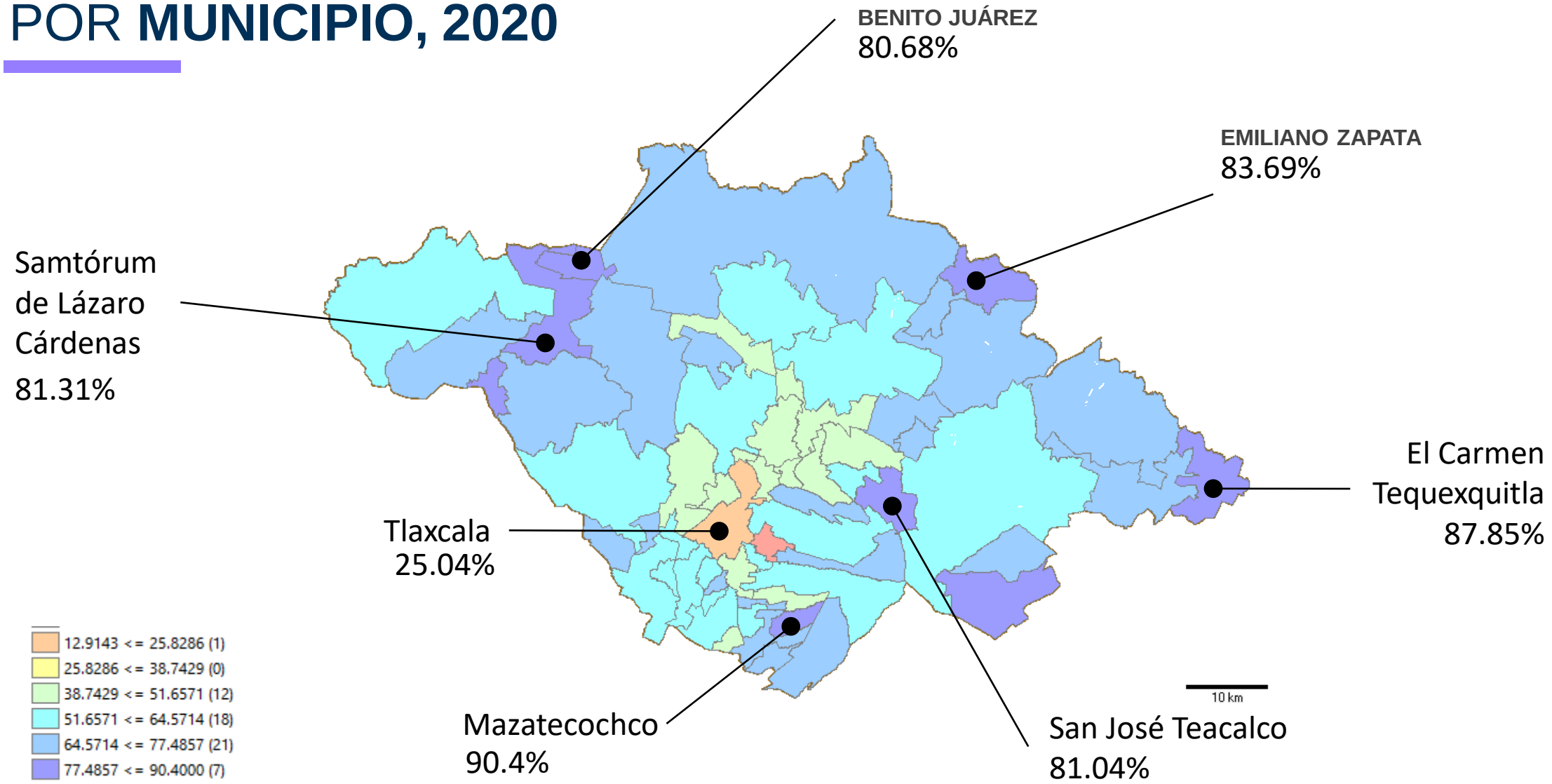

Fuente: CONEVAL. Sistema de información geográfica de Pobreza, 2020.

inegi.org.mx

PROPORCIÓN DE POBREZA EXTREMA POR **MUNICIPIO, 2020**

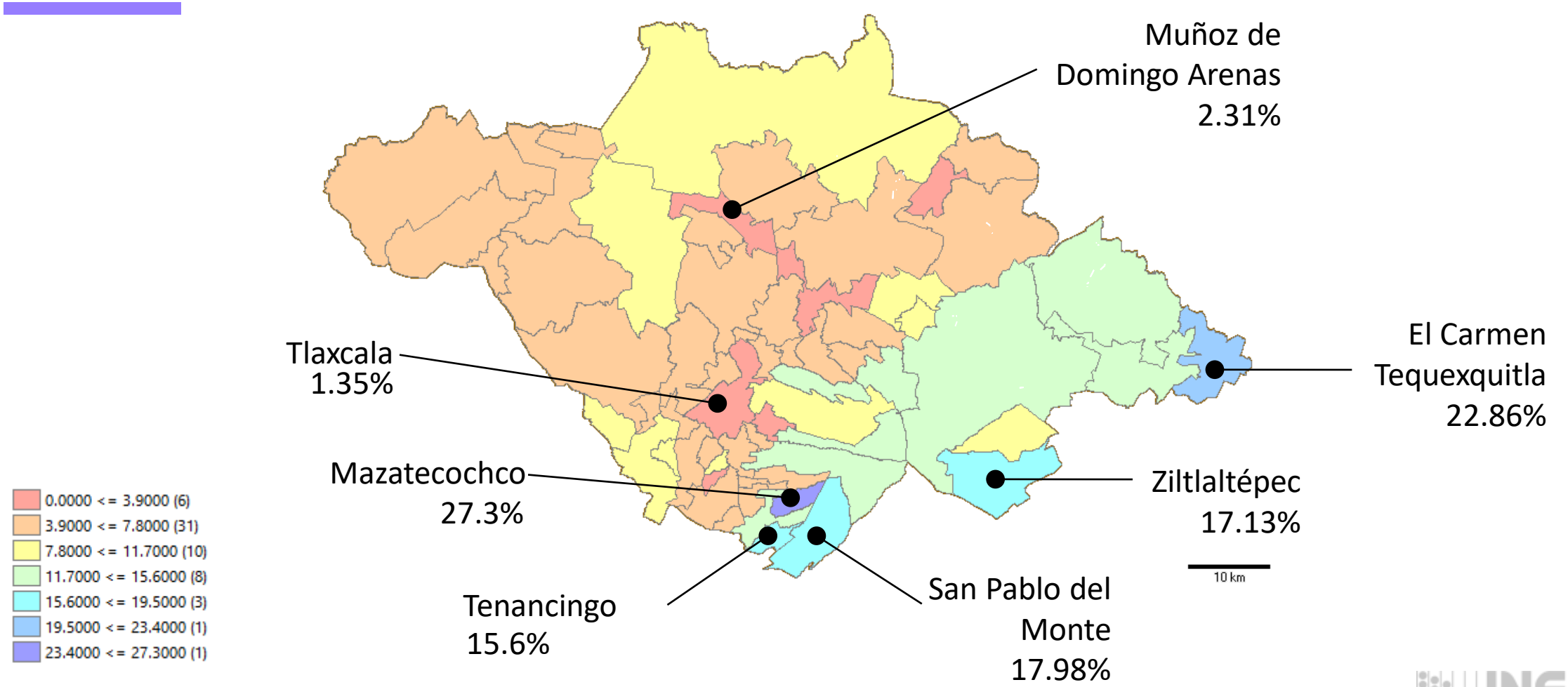

Fuente: CONEVAL. Sistema de información geográfica de Pobreza, 2020.

inegi.org.mx

¡GRACIAS!

CONOCIENDO MÉXICO

800 111 46 34

atencion.usuarios@inegi.org.mx

inegi.org.mx

INEGI

inegi.org.mx